GéoMolo

Guide enseignant — Démarrage rapide

Démarrer

Ouvrir GéoMolo

Ouvrir **geomolo.ca** dans Chrome, Edge ou Safari sur le Chromebook, l'iPad ou l'ordinateur de l'élève. Rien à installer. L'outil fonctionne aussi hors ligne après la première visite.

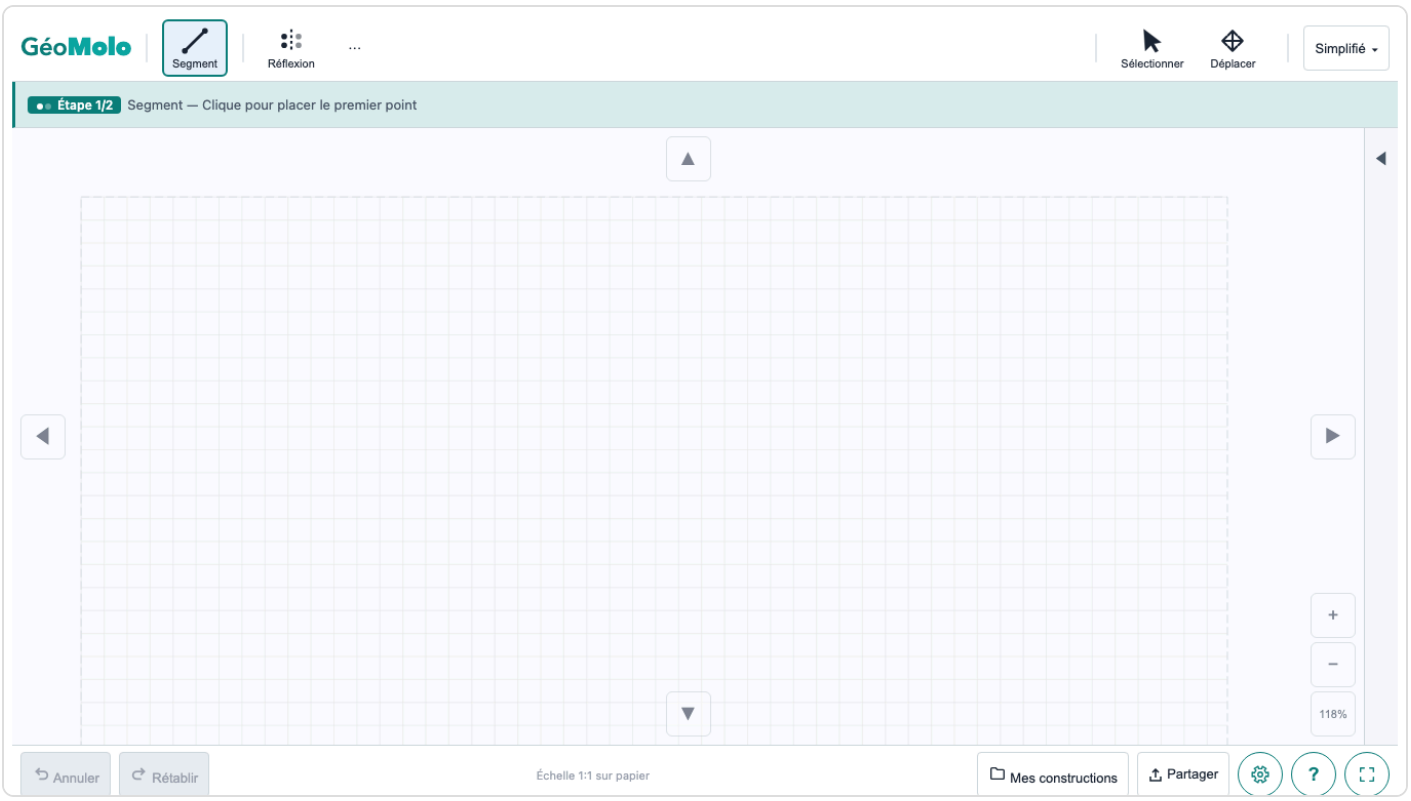

Choisir le mode d'affichage

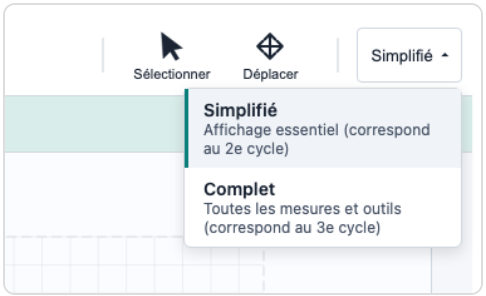

En haut à droite de la barre d'outils, un menu déroulant permet de choisir :

- **Simplifié** : affichage essentiel (correspond au 2e cycle)
- **Complet** : toutes les mesures et outils (correspond au 3e cycle)

Le mode Simplifié affiche les angles par classification (aigu, droit, obtus), sans mesure en degrés, conformément au programme du 2e cycle. Le mode Complet ajoute le cercle, la translation, la rotation, l'agrandissement et le plan cartésien. Le mode peut être changé à tout moment.

> Le vocabulaire s'adapte automatiquement au contexte : un « point » devient « sommet » quand il fait partie d'une figure fermée, un « segment » devient « côté ». C'est le vocabulaire exact du programme.

Le tutoriel intégré

À la première utilisation, un court tutoriel guide l'élève pas à pas directement dans la barre de statut (la barre verte sous les outils). L'élève apprend à tracer un segment, annuler, retracer et supprimer, en environ 30 secondes, par l'action.

La barre de statut

La barre sous les outils guide l'élève à chaque étape en langage simple :

L'élève n'a qu'à suivre l'instruction affichée.

Une construction simple

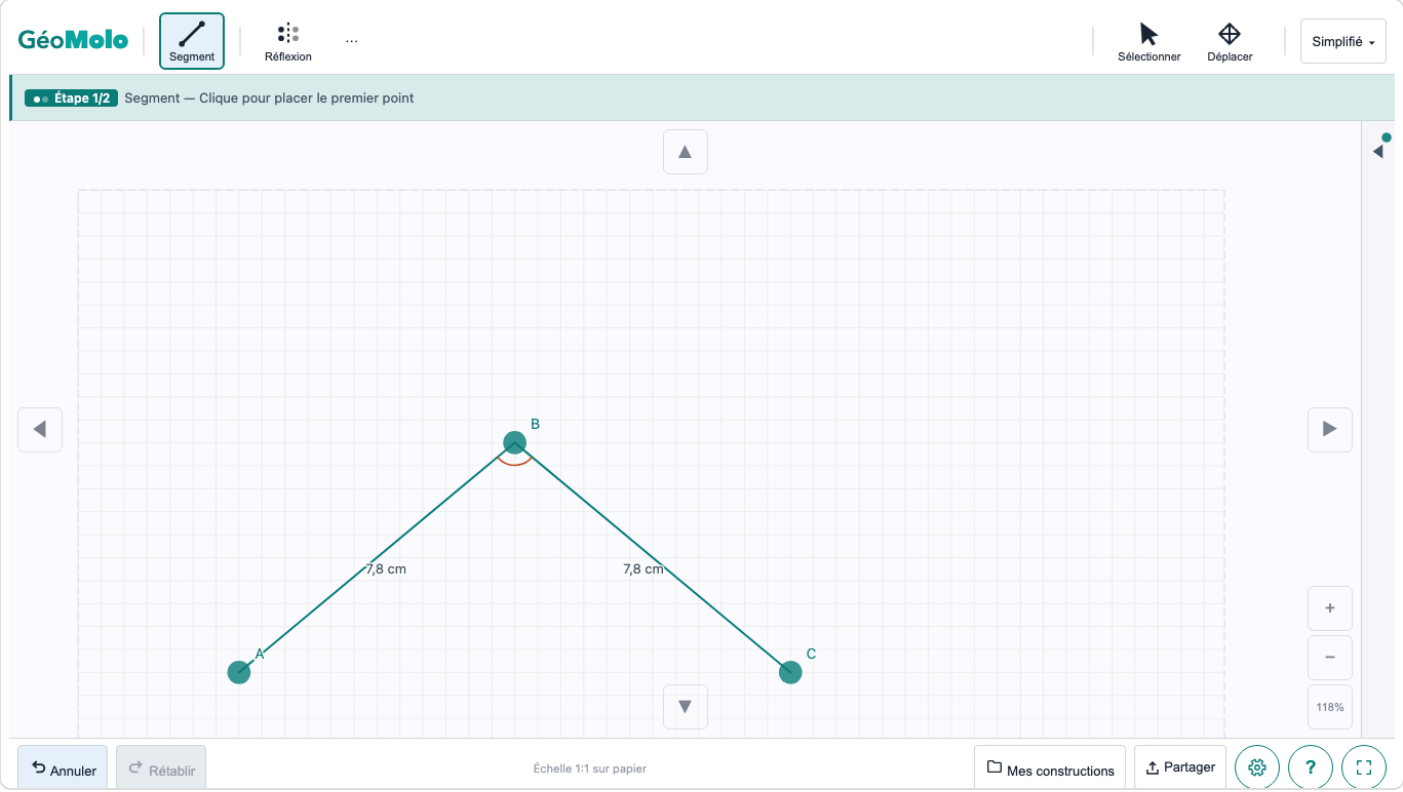

En classe

Préparer et partager une consigne

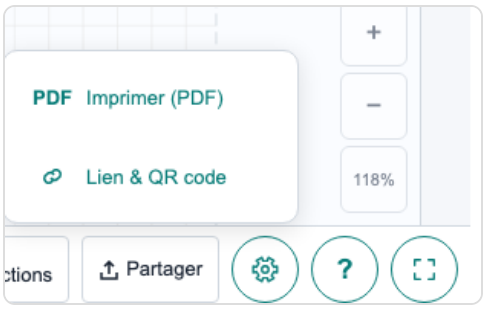

1. Construire la figure de départ dans GéoMolo
2. Écrire la consigne avec l'outil **Texte** (bouton T; en mode Simplifié, cliquer d'abord *Plus d'outils*)
3. Cliquer **Partager** → **Lien & QR code**
4. Coller le lien dans Google Classroom ou Microsoft Teams, ou afficher le code QR au tableau

L'élève ouvre le lien et voit la figure avec la consigne en bannière permanente. Il travaille directement dans son navigateur. C'est la méthode recommandée : le lien contient tout, aucune manipulation de fichier requise.

Récupérer le travail de l'élève

- **PDF 1:1** : l'élève clique **Partager** → **Imprimer (PDF)**. Un segment de 5 cm à l'écran mesure 5 cm sur papier.
- **Fichier .geomolo** : l'élève exporte sa construction (menu des constructions). Le fichier peut être rouvert dans GéoMolo.

> **Chromebook partagé ou environnement Deep Freeze :** les constructions sauvegardées dans le navigateur sont effacées au redémarrage. Demander à l'élève d'exporter son travail (fichier .geomolo ou PDF) avant de quitter la session.

Évaluation

Masquer les propriétés (dans le panneau latéral *Propriétés*, à droite) : cache les propriétés détectées (parallélisme, perpendicularité, noms de figures). L'élève voit les segments et les mesures, mais doit identifier les propriétés lui-même.

Utilisation typique : évaluation des compétences en classification géométrique.

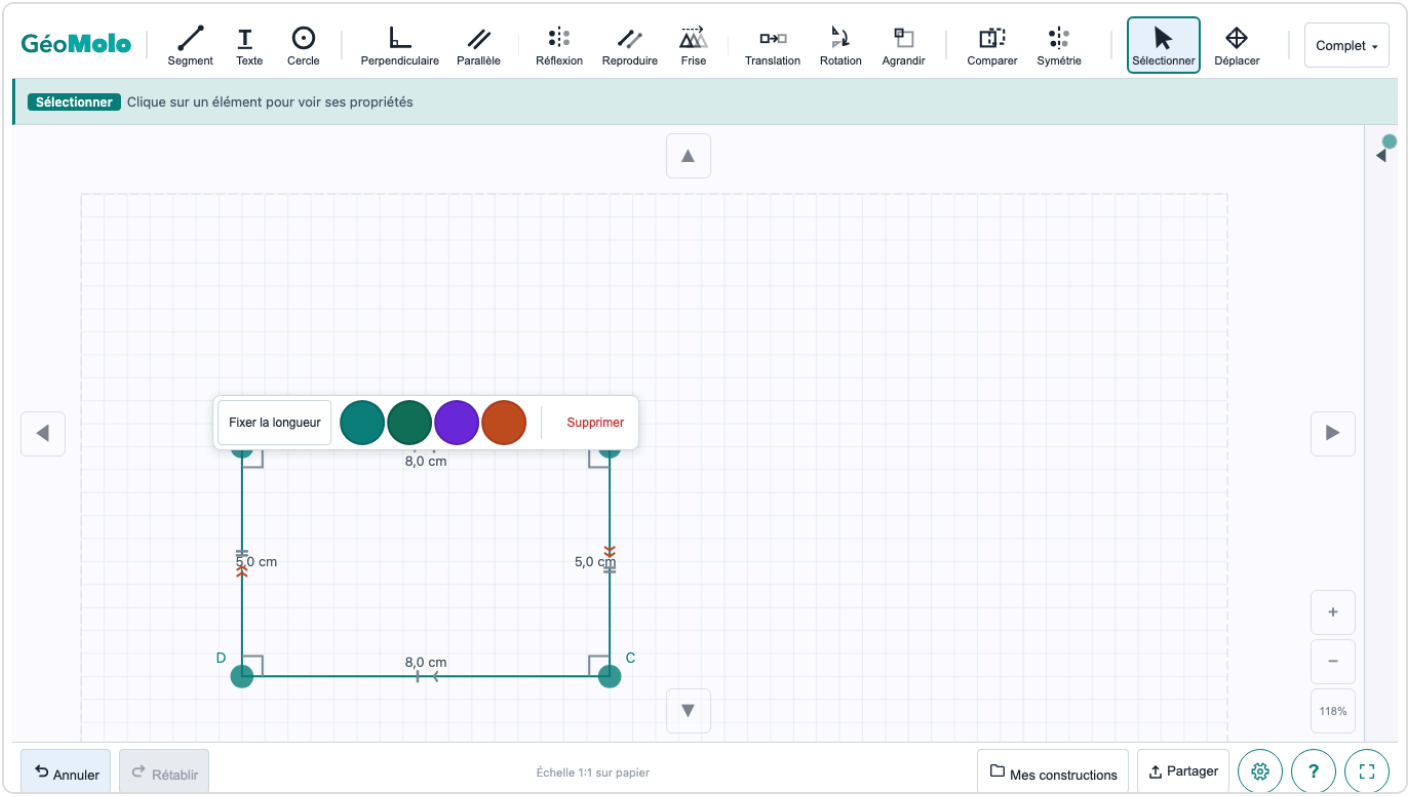

Mode estimation (dans **Paramètres** ⚙ → *Paramètres de classe*) : cache toutes les mesures. L'élève estime d'abord, puis clique « Vérifier » pour comparer avec les vraies valeurs.

Utilisation typique : développement du sens de la mesure.

> Ces deux modes permettent à l'élève d'utiliser GéoMolo en situation d'évaluation sans que l'outil ne donne les réponses à sa place.

Profils d'accessibilité

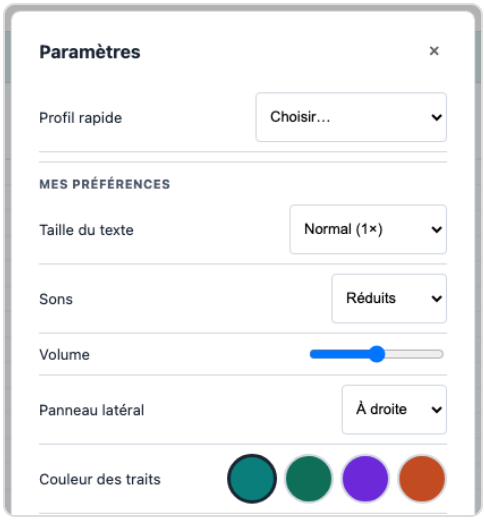

Dans **Paramètres** → **Profil rapide**, trois profils préréglés :

- **Standard** : réglages par défaut
- **Accessibilité accrue** : zones de détection plus larges, texte plus grand
- **Accessibilité maximale** : zones très larges, texte très grand, contraste élevé, rappel de pause

Avant la première utilisation par un élève ayant des difficultés, sélectionner un profil dans les Paramètres. Observer l'élève pendant les premières utilisations pour ajuster au besoin :

- **Standard** : l'élève place ses points correctement la plupart du temps
- **Accessibilité accrue** : l'élève place souvent ses points à côté de l'endroit voulu, ou doit s'y reprendre plusieurs fois
- **Accessibilité maximale** : l'élève a besoin de plus de repères visuels, se fatigue rapidement, ou a des difficultés à lire les mesures à l'écran